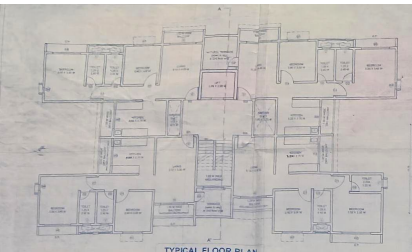

TYPICAL FLOOR PLAN
2ND, 3RD, 4TH
SCALE 1:100

P-LINE AREA DIAGRAM FOR PROP. 2nd, 3rd, 4th FLOOR AREA :

P-LINE AREA CALCULATION FOR PROP. 1st FLOOR AREA :

AREA OF RECTANGLE		SQ.M.			SQ.M.
A	27.35 x 19.25	526.64			
DEDUCTION					
1	4.00 x 2.10	12.60	11	4.00 x 0.30	25.50
2	3.00 x 1.00	3.00	12	1.75 x 0.90	3.20
3	2.00 x 0.90	1.80	13	1.75 x 0.90	1.61
4	2.00 x 0.90	1.80	14	3.35 x 0.75	2.51
5	2.00 x 0.90	1.80	15	3.35 x 0.75	2.51
6	0.90 x 0.15	0.90	16	1.75 x 0.15	0.26
7	1.40 x 0.15	0.21	17	0.90 x 0.15	0.14
8	4.00 x 1.00	25.50			
9	3.00 x 1.00	3.00			
10	1.90 x 2.75	5.23			
	TOTAL BUILT-UP AREA	455.15			

P-LINE AREA DIAGRAM FOR PROP. 1st FLOOR AREA :

1ST FLOOR PLAN
SCALE 1:100

P-LINE AREA CALCULATION FOR PROP. 7th FLOOR AREA :

AREA OF RECTANGLE		SQ.M.			SQ.M.
A	25.70 x 14.75	379.04			
DEDUCTION					
1	0.90 x 0.20	0.18	11	1.40 x 0.20	0.28
2	1.70 x 0.20	0.34	12	1.70 x 0.15	0.26
3	1.40 x 0.20	0.28	13	2.05 x 1.40	2.87
4	1.40 x 0.20	0.28	14	1.40 x 0.20	0.28
5	1.40 x 0.20	0.28	15	1.90 x 1.05	1.99
6	4.00 x 10.15	40.60	16	4.00 x 1.00	3.50
7	1.90 x 1.70	3.23			
8	1.90 x 2.15	4.08			
9	1.90 x 1.70	3.23			
10	4.40 x 0.20	0.88			
	TOTAL BUILT-UP AREA	355.55 - 71.0 = 223.38 sq.m.			

P-LINE AREA DIAGRAM FOR PROP. 7th FLOOR AREA :

STILT FLOOR PLAN
SCALE 1:200

P-LINE AREA CALCULATION FOR PROP. 6th FLOOR AREA :

AREA OF RECTANGLE		SQ.M.			SQ.M.
A	22.70 x 15.75	357.71			
DEDUCTION					
1	4.00 x 1.20	4.80	11	0.90 x 0.05	0.05
2	2.00 x 1.00	2.00	12	0.90 x 1.00	0.90
3	2.00 x 1.20	2.40	13	2.00 x 0.40	0.80
4	2.00 x 1.20	2.40	14	1.20 x 0.15	0.18
5	1.40 x 0.20	0.28	15	1.20 x 0.15	0.18
6	2.40 x 0.40	0.96	16	0.91 x 0.70	0.64
7	4.00 x 0.40	1.60	17	1.00 x 0.40	0.40
8	4.00 x 0.40	1.60			
9	1.00 x 0.70	0.70			
10	1.00 x 0.70	0.70			
	TOTAL BUILT-UP AREA	356.71 - 34.20 = 322.51 sq.m.			

P-LINE AREA DIAGRAM FOR PROP. 6th FLOOR AREA :

BLOCK PLAN
SCALE 1:200

P-LINE AREA CALCULATION FOR PROP. 5th FLOOR AREA :

AREA OF RECTANGLE		SQ.M.			SQ.M.
A	27.40 x 15.00	410.97			
DEDUCTION					
1	4.00 x 1.80	11.70	11	1.40 x 0.10	0.14
2	2.00 x 1.20	2.40	12	0.07 x 1.00	0.06
3	2.00 x 1.20	2.40	13	0.07 x 1.00	0.07
4	1.40 x 0.20	1.60	14	0.10 x 1.40	0.07
5	1.90 x 1.20	2.40	15	0.90 x 1.00	0.90
6	0.07 x 1.00	0.07	16	1.20 x 1.40	0.84
7	0.07 x 1.00	0.07	17	0.90 x 1.00	0.90
8	1.40 x 1.00	0.14			
9	1.40 x 1.00	0.14			
10	1.90 x 1.10	2.09			
	TOTAL BUILT-UP AREA	428.10 - 23.07 = 405.07 sq.m.			

P-LINE AREA DIAGRAM FOR PROP. 5th FLOOR AREA :

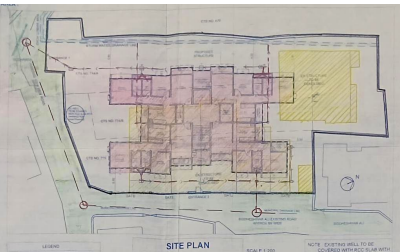

SITE PLAN
SCALE 1:200

LEGEND
- PROPOSED TOILET DRAINAGE LINE
- PROPOSED STORM WATER LINE
- MUNICIPAL DRAINAGE LINE
- PROPOSED BUILDING LINE
- PLOT BOUNDARY LINE
- EXISTING STRUCTURE TO BE DEMOLISHED

NOTE : EXISTING WELL TO BE COVERED WITH RCC SLAB WITH OPENING FOR MAINTANANCE

7th FLOOR PLAN
SCALE 1:100

6th FLOOR PLAN
SCALE 1:100

5th FLOOR PLAN
SCALE 1:100

LOCATION PLAN
SCALE 1:1000

FORM OF STATEMENT 1 Sr. No. 9 (g)

AREA DETAIL OF APARTMENT

FLOOR NO.	APARTMENT NO.	CARPET AREA OF APARTMENTS NO OF FLATS	AREA IN SQ.M	AREA OF BALCONY ATTACHED TO APARTMENTS
1	101	1 NO.	59.58	7.74 SQ.M
1	102	1 NO.	60.48	7.42 SQ.M
1,2,3,4,5	103,203,303,403,503	5 NO.S	57.33	5.85 SQ.M
1,2,3,4,5	104,204,304,404,504	5 NO.S	56.77	5.85 SQ.M
2	201	1 NO	62.85	2.70 SQ.M
2,4	201,401	2 NO.S	59.58	5.85 SQ.M
2,3,4,5	202,302,402,502	4 NO.S	59.53	5.85 SQ.M
3	301	1 NO	59.58	7.51 SQ.M
3	302	1 NO	59.53	7.34 SQ.M
4	402	1 NO	59.58	6.72 SQ.M
5	503	1 NO	40.48	5.85 SQ.M
6	604	1 NO	40.33	5.00 SQ.M
7	701	1 NO	42.77	3.24 SQ.M
7	702	1 NO	39.93	3.24 SQ.M
7	703	1 NO.	40.48	0.80 M
7	704	1 NO	38.71	0.80 M

PARKING AREA STATEMENT

		NO OF FLATS	NO. OF CAR	NO. OF SCOOTER
1	ONE PARKING AREA FOR EVERY TENEMENT			
2	FOR EVERY TENEMENT HAVING CARPET AREA OF 150 SQ.M. AND ABOVE		NIL	
3	FOR EVERY TENEMENT HAVING CARPET AREA EQUAL TO OR ABOVE 90 SQ.M BUT LESS THAN 150 SQ.M	NIL		
4	FOR EVERY 2 TENEMENT HAVING CARPET AREA EQUAL TO OR ABOVE 60 SQ.M BUT LESS THAN 90 SQ.M	27	13.50	54
5	FOR EVERY 3 TENEMENT WITH EACH TENEMENT HAVING CARPET AREA EQUAL TO OR ABOVE 40 SQ.M BUT LESS THAN 60 SQ.M	1	NIL	1
6	FOR EVERY 3 TENEMENT WITH EACH TENEMENT HAVING CARPET AREA LESS THAN 40 SQ.M BUT MORE THAN 30 SQ.M			
8	MULTIPLYING FACTOR OF 0.8		10.80	44
	TOTAL REQUIRED PARKING CAR		11.80	
	TOTAL REQUIRED PARKING SCOOTER			44
9	TOTAL REQUIRED CAR PARKING (CONSIDERING 1 CAR/4 SCOOTERS)		14.10	
7	ADDITIONAL 5% VISITOR'S PARKING (ON 9)		15.54	

DOOR- WINDOW SCHEDULE

TYPE	SIZE IN MT	DESCRIPTION OF PARTICULARS
D	0.90 X 2.10	T.W. FRAMED FULLY PANELLED SINGLE LEAF
D1	0.90 X 2.10	T.W. FRAMED FULLY PANELLED SINGLE LEAF
D2	0.75 X 2.10	ALUMINIUM FRAMED PARTLY GLAZED SWITCH DOOR
W	1.80 X 1.20	ALUMINIUM FRAMED FULLY GLAZED SLIDING WINDOW
W1	1.80 X 1.00	ALUMINIUM FRAMED FULLY GLAZED SLIDING WINDOW
W2	1.80 X 2.10	ALUMINIUM FRAMED FULLY GLAZED SLIDING WINDOW
W3	1.80 X 1.35	ALUMINIUM FRAMED FULLY GLAZED SLIDING WINDOW
W4	1.80 X 1.20	ALUMINIUM FRAMED FULLY GLAZED OPENABLE WINDOW
V	0.15 X 0.90	ALUMINIUM FRAMED GRILL VENTILATOR

FORM OF STATEMENT 2 Sr. No. 9 (a)

PROPOSED BUILDING

FLOOR	BUILT UP AREA	PERMI BALC	PROP BALC	STAIRCASE AREA	TOTAL AREA IN SQ.M
STILT					
FIRST					317.38
SECOND					306.28
THIRD					306.28
FOURTH	P-LINE AREA				306.28
FIFTH					306.91
SIXTH					304.28
SEVENTH					223.32

TOTAL BUILT-UP AREA = 2033.71 SQ.M.

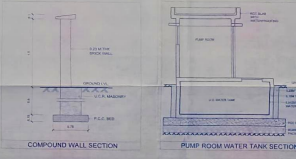

COMPOUND WALL SECTION

PUMP ROOM WATER TANK SECTION

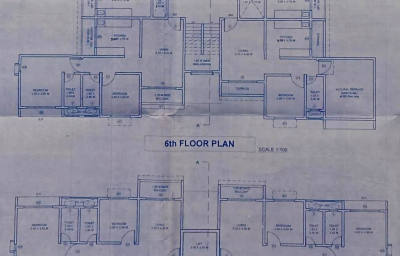

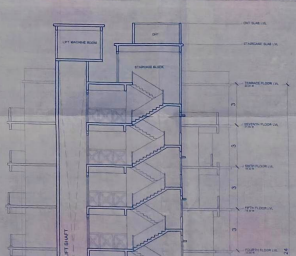

SECTION A-A'
SCALE 1:100

BUILDING PERMISSION FOR (C.C)

STAMP AND SIGNATURE :

OFFICE OF THE KALYAN DOMBIVLI MUNICIPAL CORPORATION, KALYAN.
Building Permit No. KDMC/TP/BP/KD/2023-24/27
Date : 25/05/2023
SANCTIONED

ASSISTANT DIRECTOR OF TOWN PLANNING
Kalyan-Dombivli Municipal Corporation.

PROFORMA - I

AREA STATEMENT

		SQ.M.
1	Area of the plot (minimum area of 4 % of to be considered)	
a	Total area of plot as per ownership documents (Ha)	10334.20
b	Area of plot in possession as no. 715	3380.10
c	Area of plot in city & no. 714 A & 714 B	6954.10
d	Area of plot as per measurement sheet	
e	Area of plot as per site	
2	Deductions for	
a	Proposed D.P. / D.P. Road widening area (As per DP remark)	0.00
b	Any D.P. Reservation area	0.00
	Total (a + b)	0.00
3	BALANCE AREA OF PLOT	10334.20
4	Amenity Space (If applicable)	
a	Required	1034.20
b	Balance proposed	
5	Net plot area (3 - 4 (b))	10334.20
6	Recreational open space (if applicable)	
	Required	0.00
	Proposed	0.00
	Internal Road Area	0.00
7	Permissible Area (If applicable)	
	F.S.I on C.S. No. 715 (area in gaothan)	1.30
a	1.50 Basic FSI on net plot (as per UDCPR 2020) (Ha=1Ha) 3380.10 x 1.5	5074.15
b	Add 50% of ancillary FSI on basic FSI (60% on 5074.15)	3044.49
10	Total permissible area for gaothan plot (Ga+4b)	8118.64
11	F.S.I on C.S. No. 714 A & 714 B. (area in city)	1.10
a	1.00 Basic FSI on net plot (as per in city MTP) 6954.10 x 1 (as per UDCPR 2020)	6954.10
b	Add 50% of ancillary FSI on basic FSI (60% on 6954.10)	4830.75
12	Total permissible area for city plot (11a+11b)	11784.85
13	Addition of FSI on payment of Premium	0.00
14	Prefix F.S.I TDR loading	0.00
15	Total permissible P-LINE Area (10+12+13+14)	20903.50
16	Total Built-up Area in proposal	
a	Existing Built-up Area (to be retained)	0.00
b	Proposed Built-up Area (as per P-Line)	2033.71
c	Total Built-up area (a+b)	2033.71

	Parking Statement	
	Required car parking for tenements	11
	Required scooter parking for tenements	45
	Required 5% visitor's Parking	1
	Proposed no.of car parkings for tenements (considering 1 car / 4 scooters)	10

APPENDIX - C

I HEREBY CERTIFY THAT THE STRUCTURAL DRAWINGS FOR THE ABOVE MENTIONED WORK ARE PREPARED BY ME / US AND THE WORK AS FAR AS STRUCTURAL DRAWINGS ARE CONCERNED, SHALL BE CARRIED OUT AS SPECIFIED IN APPENDIX 'C' AND AS PER INDIAN STANDARD INSTITUTE. I SHALL BE RESPONSIBLE FOR ADEQUACY OF THE STRUCTURAL DESIGN AS FAR AS STRUCTURAL DRAWINGS ARE CONCERNED.

SIGNATURE OF ENGINEER

CERTIFICATE OF AREA

I HEREBY CERTIFY THAT I HAVE SURVEYED THE PLOT UNDER REFERENCE JAN 2023 AND THAT THE DIMENSIONS OF SIDES ETC. OF THE PLOT STATED ON THE PLAN ARE AS MEASURED ON SITE AND THE AREA SO MEASURED DUE IS 1034.20 SQ.FT AND TALLIES WITH THE DOCUMENT OF OWNERSHIP. TOWN SCHEME RECORDS

SIGNATURE OF ARCHITECT

DESCRIPTION OF PROPOSAL AND PROPERTY

PROPOSED DEVELOPMENT SCHEME ON CTS. NO. 715, 714 (A),714 (B) AT PARNAKA KALYAN, TAL.-KALYAN, DIST.-THANE.

NAME OF OWNER: SHRI. MARATHE AND OTHERS

NAME OF POA HOLDER: SHRI. PRAKASH LELE
M/S APPLE CONSTRUCTION

CONTENTS OF SHEET
SITE AND LOCATION PLAN , FLOOR PLANS
AREA STATEMENT ,AREA DIAGRAM AND CALCULATIONS
SECTIONS, DOOR- WINDOW SCHEDULE, PARKING AREA STATEMENT, FORM OF STATEMENT- 1 & 2.

NOTES .. ALL DIMENSIONS ARE IN METERS.

OWNER'S / POA SIGN . ARCHITECT'S SIGN

M/S APPLE CONSTRUCTION — A.P. SAHASRABUDDHE

SAHASRAARCH
A.P.SAHASRABUDDHE
ARCHITECT
INTERIOR DESIGNER
SHOP NO. 31, 32, SHIVAJI CHOWK, KALYAN- 421301

DRAWN BY	CHECKED BY	NORTH
SARNALI	A.P.S	
SCALE :	DATE	JOB NO	D.W.G. NO.
AS MENTIONED	28.09.2023	0711/1/1/1/5	1

KALYAN DOMBIVALI MUNICIPAL CORPORATION, KALYAN

APPENDIX 'D-1'

FORM FOR SANCTION OF BUILDING PERMISSION AND COMMENCEMENT CERTIFICATE

To,
Mr. Bhaskar Marathe & Other
P.O.A. - M/s. Apple Construction through
Mr. Prakash Padmakar Lele.
Architect – Mr. Anand Sahastrabuddhe, Kalyan (W)
Structural Engineer – M/s. Khasnis & Associates, Kalyan.

With reference to your application dated 28/03/2023 for the grant of sanction of Commencement Certificate under Section 44 of The Maharashtra Regional and Town Planning Act, 1966 read with Section 253 of Maharashtra Municipal Corporations Act, 1949 to carry out development work / Building on CTS.No.714/A, 714/B, & 715 Village - Kalyan, Situated at Kalyan (W), the Commencement Certificate / Building Permit is granted under Section 45 of the said Act, subject to the following conditions:

1. The land vacated in consequence of the enforcement of the set-back rule shall form part of the public street in future.
2. No new building or part thereof shall be occupied or allowed to be occupied or used or permitted to be used by any person until occupancy certificate is granted.
3. The Commencement Certificate/ Building permit shall remain valid for a period of one year commencing from the date of its issue unless the work is not commenced within the valid period.
4. This permission does not entitle you to develop the land which does not vest in you.

Office No. KDMC/TPD/BP/KD/2023-24/27.

Office Stamp

Date : 25/05/2023.

Yours faithfully,

KALYAN DOMBIVALI MUNICIPAL CORPORATION
कल्याण डोंबिवली महानगरपालिका
जि. ठाणे.
DIST. THANE

for Assistant Director of Town Planning
Kalyan Dombivali Municipal Corpoation, Kalyan.

कल्याण डोंबिवली महानगरपालिका, कल्याण

नगररचना विभाग

बांधकाम प्रारंभ प्रमाणपत्रनी क्र:KDMC/TPD/BP/KD/2023-24/27.

Dt 25/05/2023.

महाराष्ट्र प्रादेशिक व नगररचना अधिनियम १९६६ चे कलम ४४ तसेच म.प्रा. व न.र. अधिनियम १९६६ चे कलम ४५ नुसार सि.स.नं. ७१४/अ, ७१४/ब, ७१५, मौजे कल्याण (प.) मध्ये मालमत्ता पत्रकानुसार १०३४.२० चौ.मी. क्षेत्रापैकी ३६२.१० चौ.मी. क्षेत्र गावठाण मध्ये समाविष्ठ असून ६७२.१० चौ.मी. क्षेत्र गावठाणाबाहेरील आहे. त्यानुसार **Basic FSI** व **Ancellary FSI** चा विचार करुन एकूण २०३३.७१ चौ.मी. बांधकाम क्षेत्रासह भूखंडाचा विकास करावयास दिनांक ०२/०१/२०२३ च्या अर्जास अनुसरुन खालील अटी व शर्तीस अधिन राहून, तसेच नकाशावर हिरव्या रंगाने दुरुस्ती दाखविल्याप्रमाणे वाडे–भिंतीच्या बांधकामासह, बांधकाम प्रारंभ प्रमाणपत्र देण्यात येत आहे.

बांधकामाचा तपशील :–

- इमारत – स्टिल्ट + पहिला मजला ते सातवा मजला (रहिवास)

अटी व शर्ती :–

१) एकत्रिकृत विकास नियंत्रण व प्रोत्साहन नियमावली **(UDCPR)** मधील विनियम क्र. २.८.३ नुसार प्रत्यक्ष जागेवर बांधकाम सुरु करणेपुर्वी बांधकाम मंजुरीचा फलक लावणे आपणांवर बंधनकारक राहिल.

२) **UDCPR** मधील विनियम क्र.**1.5 Savings** मध्ये नमूद **a to h** बाबत शासनाच्या वेळोवेळी निर्गमित होणाऱ्या मार्गदर्शक सूचना आपणांवर बंधनकारक राहील.

३) बांधकाम चालू करण्यापूर्वी सात दिवस आधी महापालिका कार्यालयास लेखी कळविण्यात यावे.

४) **UDCPR** मधील **Appendix-F** नुसार वाडेभिंत व जोत्याचे बांधकाम झाल्यानंतर वास्तुशिल्पकाराचे प्रमाणपत्र महानगरपालिकेस सादर करण्यात यावे व त्यानंतरच पुढील बांधकाम करण्यात यावे.

५) सदर अभिन्यासात कोणत्याही प्रकारचा फेरफार पूर्व परवानगी घेतल्याशिवाय करु नये, तसे केल्याचे आढळून आल्यास सदरची विकास परवानगी रद्द समजण्यात येईल.

६) **UDCPR** मधील विनियम क्र. १२.१ ते १२.३ नुसार इमारतीच्या बांधकामाच्या सुरक्षिततेची (स्ट्रक्चरल सेफ्टी) जबाबदारी सर्वस्वी वास्तुशिल्पकार, **Structural Engineer** व परवानगीधारक यांचेवर राहिल, याची नोंद घ्यावी.

७) सदर जागेतून पाण्याचा नैसर्गिक निचरा होत असल्यास तो जलनि:सारण विभाग,(क.डों.म.पा.) यांचे परवानगीशिवाय वळवू अथवा बंद करु नये.

८) भूखंडाकडे जाण्या–येण्याच्या मार्गाची जबाबदारी संपूर्णपणे आपलेकडे राहिल. सुधारीत बांधकाम प्रमाणपत्र नियोजित रस्त्याप्रमाणे दिले असल्याने सदर रस्त्याचे काम महानगरपालिकेच्या सोयी प्रमाणे व प्राधान्याप्रमाणे केले जाईल व तसा रस्ता होईपर्यंत इमारतीकडे येणा–जाण्याचे मार्गाची जबाबदारी सर्वस्वी आपली राहिल.

९) बांधकामाचे साहित्य रस्त्यावर टाकावयाचे झाल्यास महापालिकेच्या बांधकाम खात्याची परवानगी घेणे आवश्यक राहील व त्याकरीता नियमाप्रमाणे लागणारी रक्कम (दंड झाल्यास त्यासह रक्कम) भरावी लागेल तसेच निरूपयोगी साहित्य महापालिका सांगेल त्या ठीकाणी स्वखर्चाने वाहून टाकणे आपणावर बंधनकारक राहील.

१०) बांधकाम पूर्णत्वाचा दाखला घेण्यापुर्वी कर विभाग, जलनि:सारण विभाग व मलनि:सारण विभाग, अग्निशमन विभाग, पाणी पुरवठा विभाग, उद्यान विभाग, क.डों.म.पा. यांचेकडील ना–हरकत दाखला बांधकाम नकाशासह सादर करणे आपणावर बंधनकारक राहील.

११) ओल्या व सुक्या कचऱ्यासाठी स्वतंत्र कचराकुंडयांची व्यवस्था करणे आपणावर बंधनकारक राहील.

१२) बांधकाम पूर्णत्वाचा दाखला घेणेपूर्वी कल्याण डोंबिवली महानगरपालिकेच्या निर्देशाप्रमाणे इमारतीत सौरउर्जा उपकरणे बसवून विद्युत विभागाकडील ना हरकत दाखला सादर करणे बंधनकारक राहील.

१३) बांधकाम पूर्णत्वाचा दाखला घेणेपूर्वी UDCPR मधील विनियम क्र. १३.३ नुसार भुखंडावरील इमारतीत रेन वॉटर हार्वेस्टिंगबाबत अंमलबजावणी करणे आपणांवर बंधनकारक राहील.

१४) बांधकाम पूर्णत्वाचा दाखला घेणेपूर्वी UDCPR मधील विनियम क्र. १३.५ नुसार घनकचरा व्यवस्थापना बाबत कार्यवाही करणे तसेच संबंधित विभागाचा ना हरकत दाखला सादर करणे आपणांवर बंधनकारक राहील.

१५) नकाशात हिरव्या रंगाने केलेल्या दुरूस्त्या आपल्यावर बंधनकारक राहतील.

१६) इमारतीचे बांधकाम या सोबतच्या मंजूर केलेल्या नकाशांप्रमाणे आणि वरीलप्रमाणे घालून दिलेल्या अटींप्रमाणे करणे आपणावर बंधनकारक राहील.

१७) बांधकाम पूर्णत्वाचा दाखला घेणेपूर्वी महसूल विभागाकडून गौणखनिज स्वामित्वधन रक्कम शासनास जमा केलेबाबतचा ना हरकत दाखला सादर करणे आपणावर बंधनकारक राहील.

१८) बांधकाम पूर्णत्वाचा दाखल्यापूर्वी मा. जिल्हाधिकारी, यांचेकडील सनद सादर करणे आपणावर बंधनकारक राहील.

१९) सदर प्रकरणी चुकीची व अपुर्ण माहिती दिली असल्यास सदर बांधकाम परवानगी रद्द समजण्यात येईल.

२०) जागेच्या मालकी हक्काबाबत काही वाद असल्यास अथवा निर्माण झाल्यास त्यांचे संपूर्ण निराकरण करण्याची जबाबदारी आपली राहील. याबाबत आपण रुपये ५००/– च्या मुद्रांक पत्रावर हमीपत्र सादर केले आहे.

२१) प्रकरणी भूखंडाच्या पोहच रस्त्याबाबत भविष्यात कोणाचीही तक्रार आल्यास त्याचे निराकरण करणेची संपूर्ण जबाबदारी आपली राहील. याबाबत आपण रुपये १००/– च्या मुद्रांक पत्रावर हमीपत्र सादर केले आहे.

२२) प्रकरणी इमारतीचे बांधकाम करतेवेळी महिला कामगारांकरीता स्वतंत्र स्वच्छतागृह व खोलीचे तात्पुरत्या स्वरुपाचे बांधकाम करणे आपणावर बंधनकारक राहील.याबाबत आपण रुपये १००/– च्या मुद्रांक पत्रावर हमीपत्र सादर केले आहे.

२३) प्रकरणी जागेवर बांधकाम सुरु करणेपूर्वी बांधकाम मंजूरीचा फलक लावणे आपणावर बंधनकारक राहील.

२४) प्रकरणी न.भू.क्र. ७१५ मधील विद्यमान विहीरीवर लोखंडी जाळी बसविणे आपणावर बंधनकारक राहील.

टिप:– UDCPR नुसार वरीलपैकी आपणास लागु असलेल्या अटींची पूर्तता करणे आपणावर बंधनकारक राहील, याची नोंद घ्यावी.

इशारा:–मंजूर बांधकाम प्रस्तावाव्यतिरिक्त केलेल्या अनधिकृत फेरबदलांबाबत आपण महाराष्ट्र प्रादेशिक नियोजन व नगररचना अधिनियम, १९६६ मधील कलम–५१ ते ५७ च्या तरतूदी नुसार दखलपात्र गुन्हयास पात्र राहाल.

बांधकाम परवानगीअंतर्गत भरण्यात आलेल्या रक्कमेचा तपशिल:–

अ.क्र.	लेखाशिर्ष	रक्कम	पावती क्र.	दिनांक	यापुर्वीचा एकुण भरणा तपशिल	शेरा
१	ARI 020101	10,31,738/-	AC6599	24/05/2023		
२	ARI 020103	10,170/-	AC6599	24/05/2023		
३	ARI 020104	17,19,000/-	AC6599	24/05/2023		
४	ARI 020109					
५	ARI 020110					
६	ASI 010304	8,13,600/-	AC6598	24/05/2023		
७	ASI 010513	5,41,451/-	AC6599	24/05/2023		
८	ASI 010518	10,31,738/-	AC6597	24/05/2023		
९	ASI 020519					
	Total	51,47,696/-				

सहाय्यक संचालक नगररचना (फरिता)
कल्याण डोंबिवली महापालिका, कल्याण.

प्रत :–
१) करनिर्धारक व संकलक क.डो.म.पा.कल्याण.
२) प्रभाग क्षेत्र अधिकारी 'ब' प्रभाग क्षेत्र.